SCHOOL OF **DATA**

PRÉSENTATION DE DONNÉES ET CARTOGRAPHIE

I. RAPPEL : LA DATA PIPELINE

II. PRESENTER LES DONNEES

III. VISUALISER LES DONNÉES

IV. CARTOGRAPHIER LES DONNEES

SCHOOL OF **DATA**

LA DATA PIPELINE

OÙ ON EST-ON

CE QUE VOUS AVEZ DEJA VU

Qu’est-ce que l’open data ?
Définir son projet d’enquête
Trouver les sources de données
Récupérer les données
Vérifier les données
Nettoyer les données
Analyser les données

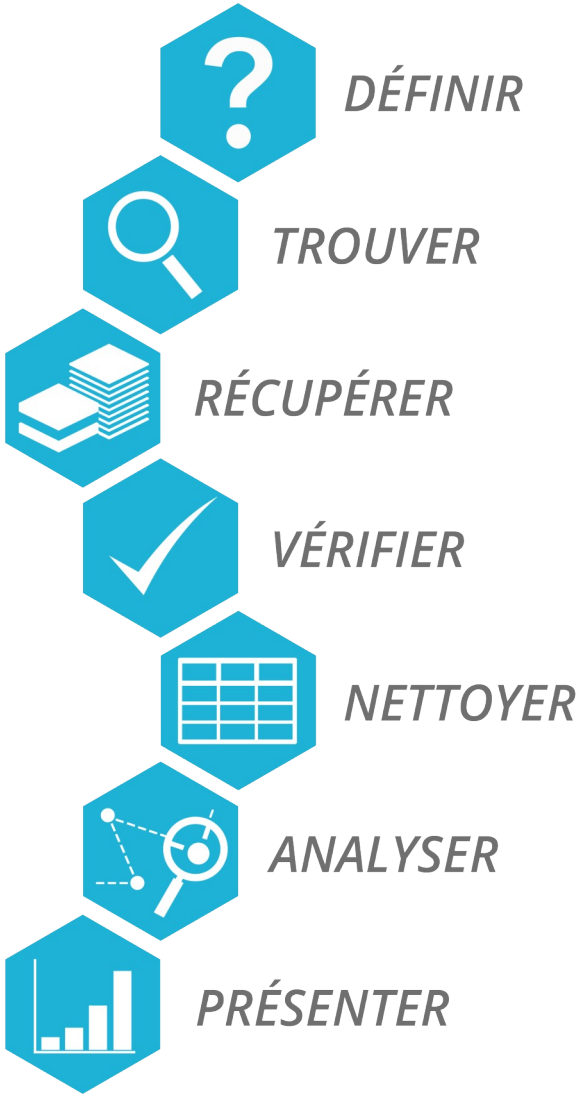

CE QUE VOUS AVEZ DÉJÀ VU

Qu’est-ce que l’open data ?
Définir son projet d’enquête
Trouver les sources de données
Récupérer les données
Vérifier les données
Nettoyer les données
Analyser les données
Présenter les données

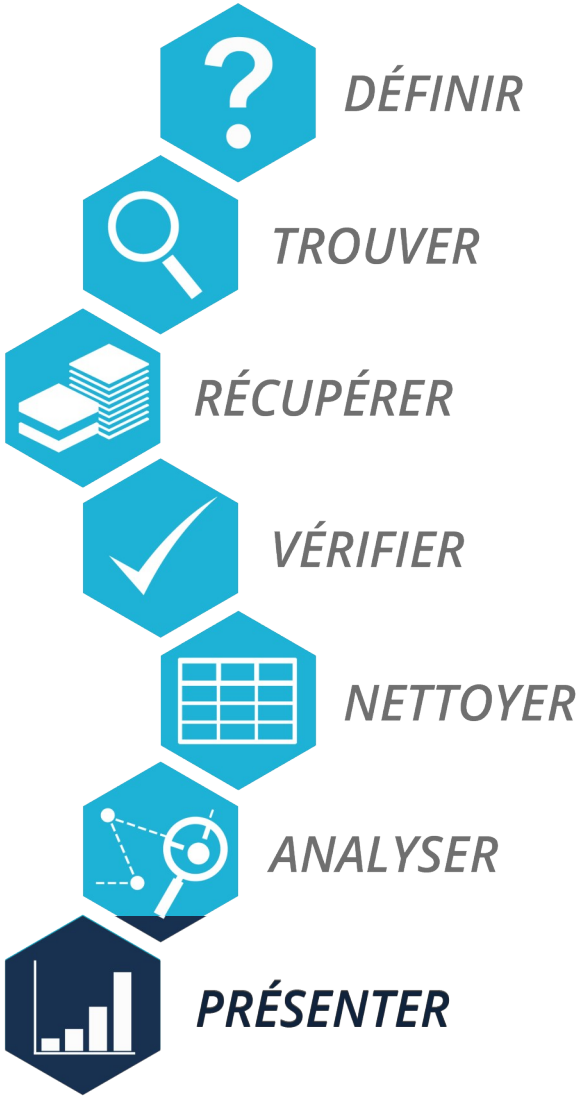

SCHOOL OF **DATA**

POURQUOI PARLER DE PRESENTATION

(et pas de visualisation?)

Parce que parfois, le message à tirer des données est plus important que leur représentation stricte

Parce que souvent, visualiser des données n’est intéressant que pour un nombre d’angles limité de votre sujet d’enquête.

Sur 8 articles du dossier « conflits d’intérêts dans l’hôpital public » de Sud Ouest, seuls 3 incluent des visualisations de données

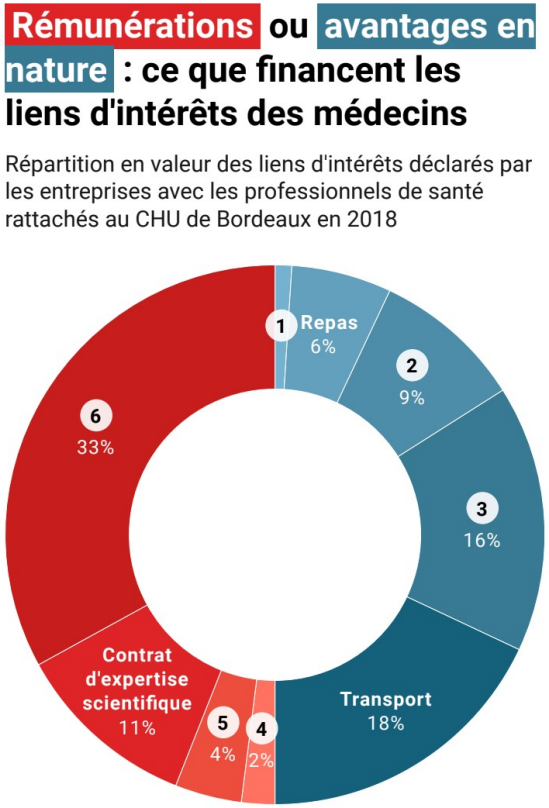

Parce que les données peuvent parfois ne représenter qu’une simple étape de votre travail d’enquête: elle ne sont pas une fin en soi.

De la même façon que vous n’essayez pas de retranscrire toutes les interviews de témoins dans l’article final, les données n’ont pas nécessairement à être mises en avant.

3 ELEMENTS CLES

Les données

La mise en forme

Le message

Les trois sont à prendre en compte à chaque fois que vous voulez présenter des données, mais une emphase peut-être mise sur un aspect plutôt que les autres.

Si vous mettez l’emphase sur...

LES DONNEES

La mise en forme

Le message

visualisations simples mais qui détaillent les chiffres ou visualisations qui permettent l’exploration par le lecteur via l’interactivité

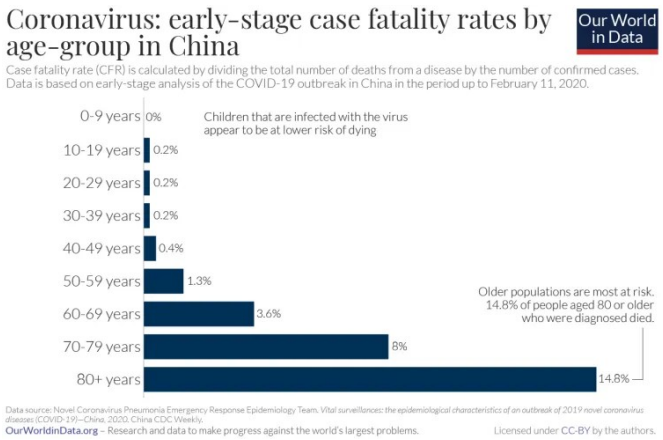

Si vous mettez l’emphase sur...

Les données

LA MISE EN FORME

Le message

visualisations qui ont pour but d’attirer le regard et de marquer l’esprit



Si vous mettez l’emphase sur...

Les données

La mise en forme

LE MESSAGE

→ infographies qui respectent les données mais ne cherchent pas à les représenter strictement

→ storytelling de données

SCHOOL OF **DATA**

OUI MAIS COMMENT

VISUALISER LES DONNÉES

Revenons à notre fichier précédent sur les régionales de 2015: http://bit.ly/IJBA2021_2015viz

Démonstration guidée de visualisation dans:

Google spreadsheet: comment se répartissent les voix dans les différentes régions de France ?

RawGraph (https://app.rawgraphs.io/): quels sont les courants les plus populaires au sein de l'échiquier politique ?`

Google Data Studio (https://datastudio.google.com): dans quelle régions trouve-t-on le plus de têtes de listes femmes ? (http://bit.ly/IJBA2021_studio)

Une emphase sur le message dépend beaucoup plus de l'angle journalistique choisi.

Exemple: une storymap qui part du nombre de têtes de listes femmes par couleur politique avant de zoomer sur des candidats indivduels

https://storymap.knightlab.com

Plein d’autres outils existent…

Dataviz: Spreadsheet, Data Studio, Datawrapper, Tableau, Raw Graphs

Infographies: Infogram, PiktoCharts

Storytelling: TimelineJS, StorymapJS

etc

SCHOOL OF **DATA**

QU'EN EST-IL DE LA

CARTOGRAPHIE DE DONNÉES

Il existe aussi plein d’outils de cartographie. Cela va du très simple

- Umap
- Khartis

Au plus complexe

- QGIS
- outils très spécialisés (e.g. éditeur de tuiles)

Quelques notions générales

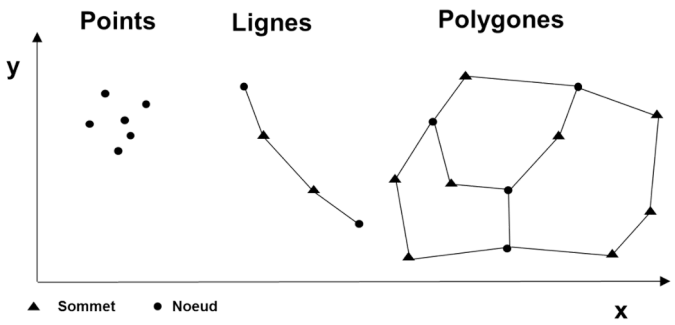

Qui dit cartographie dit données géographiques

niveau 0: latitude et longitude

niveau 1: point, lignes, polygons (géométries)

niveau 2: noms communs (adresses, noms administratifs…)

Qui dit cartographie dit projection

La projection Web Mercator est la plus connue, mais elle déforme les pôles

Qui dit cartographie dit projection

La projection Web Mercator est la plus connue, mais elle déforme les pôles

d'autres projections existent, et on d'autres usages

L'équilibre est généralement entre la préservation des angles vs les distances

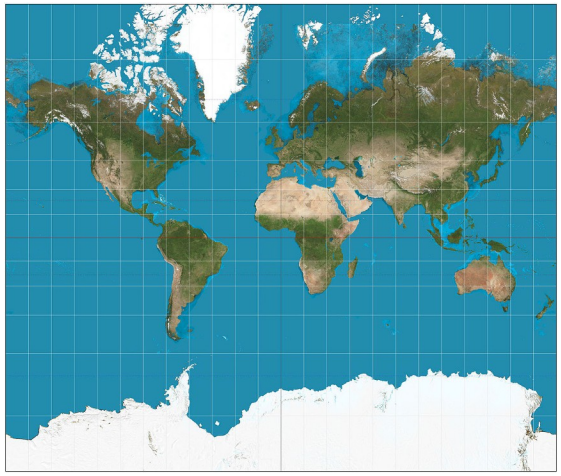

Qui dit cartographie dit fichiers géographiques

- shapefiles
- klm
- geojson
- csv avec colonnes lat/lon

	GID	IDENT	TYPEA	Geo Point	Geo Shape
1	200	BR21		44.8874536, -0.6196931	{"type":"Point","coordinates":[-0.6196
2	204	BR05		44.884951, -0.6182612	{"type":"Point","coordinates":[-0.6182
3	216	EY02		44.8626499, -0.6478524	{"type":"Point","coordinates":[-0.6478
4	234	EY12		44.8838403, -0.6447581	{"type":"Point","coordinates":[-0.6447
5	235	EY19		44.8770804, -0.6401596	{"type":"Point","coordinates":[-0.6401
6	239	EY15		44.8817623, -0.63386	{"type":"Point","coordinates":[-0.6338
7	240	EY14		44.8829196, -0.6363782	{"type":"Point","coordinates":[-0.6363
8	247	BX48		44.8736727, -0.5496006	{"type":"Point","coordinates":[-0.5496
9	248	BX46		44.8741889, -0.545997	{"type":"Point","coordinates":[-0.5459
10	263	BX58		44.8630262, -0.5670647	{"type":"Point","coordinates":[-0.5670
11	264	BX59		44.8618998, -0.5709238	{"type":"Point","coordinates":[-0.5709
12	273	VO53		44.7836968, -0.54095	{"type":"Point","coordinates":[-0.5409
13	275	TA54		44.7949569, -0.5838976	{"type":"Point","coordinates":[-0.5838
14	278	TA08		44.7939295, -0.5904067	{"type":"Point","coordinates":[-0.5904
15	298	BE15		44.8058182, -0.5657914	{"type":"Point","coordinates":[-0.5657
16	305	BE24	ENTERRE	44.8113172, -0.5666311	{"type":"Point","coordinates":[-0.5666
17	308	BE28		44.8091029, -0.5544917	{"type":"Point","coordinates":[-0.5544
18	324	LT11		44.9063707, -0.6762894	{"type":"Point","coordinates":[-0.6762

On va tester Khartis, qui a les délimitations administratives les plus à jour

Quelles proportions de têtes de listes hommes ou femmes dans chaque région ?

http://www.sciencespo.fr/cartographie/khartis

SCHOOL OF **DATA**

C’EST DEJA FINI

MERCI